Конференции большой тройки: СССР, США и Великобритания

Тегеранская конференция

Конференция была призвана разработать окончательную стратегию для борьбы против Германии и её союзников.

Проводилась с 28 ноября по 1 декабря 1943г. в иранском городе Тегеран.

Основные военные и политические решения

- Открытие второго фронта
- Раздел Германии
- Решение вопроса по границам Польши
- Вступление СССР в войну против Японии
- Декларация трех держав

Открытие второго фронта

Открыт **6 июня 1944 года**.

Это событие вошло в историю как **«День Д»** и ознаменовало начало масштабной Нормандской десантной операции, кодовое название которой было **«Оверлорд»**

6 июня 1944 г. - высадка англо-американских войск в **НОРМАНДИИ** на севере **ФРАНЦИИ**.

Раздел Германии

Президент США Франклин Рузвельт предложил разделить Германию на следующие части: Ганновер, Пруссия, Гессен, Саксония и Бавария.

В Тегеране окончательное решение принято не было. Вопрос передали в Европейскую консультативную комиссию.

Решение вопроса по границам Польши

Восточная граница - «линия Керзона». Вхождение территорий Западной Украины и Западной Белоруссии в состав СССР.

Западная граница - до реки Одер. Польша получает земли на западе за счёт Германии

Также под власть СССР отошёл Кёнигсберг.

Декларация трёх держав

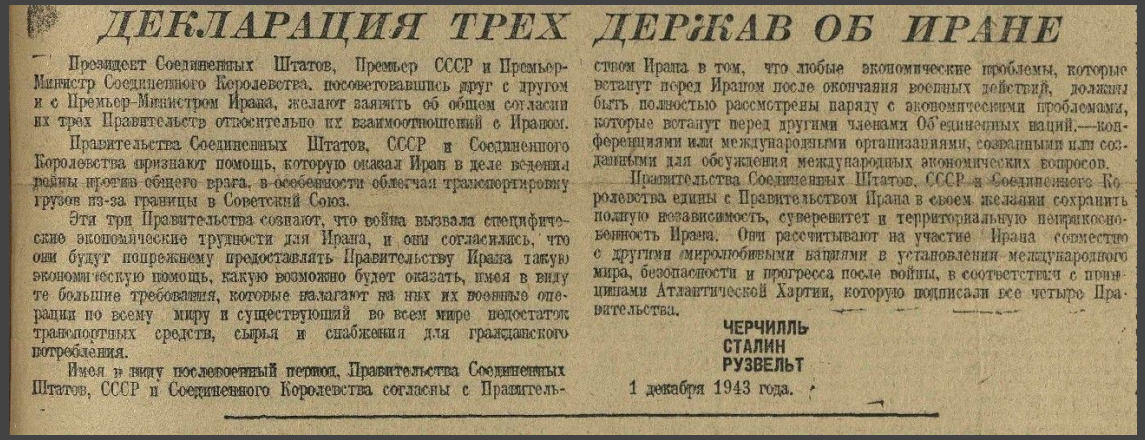

ДЕКЛАРАЦИЯ ТРЕХ ДЕРЖАВ ОБ ИРАНЕ

Президент Соединенных Штатов, Премьер СССР и Премьер-Министр Соединенного Королевства, посоветовавшись друг с другом и с Премьер-Министром Ирана, желают заявить об общем согласии их трех Правительств относительно их взаимоотношений с Ираном.

Правительства Соединенных Штатов, СССР и Соединенного Королевства признают помощь, которую оказал Иран в деле ведения войны против общего врага, в особенности облегчая транспортировку грузов из-за границы в Советский Союз.

Эти три Правительства сознают, что война вызвала специфические экономические трудности для Ирана, и они согласились, что они будут попрежнему предоставлять Правительству Ирана такую экономическую помощь, какую возможно будет оказать, имея в виду те большие требования, которые налагают на них их военные операции по всему миру и существующий во всем мире недостаток транспортных средств, сырья и снабжения для гражданского потребления.

Имея в виду послевоенный период, Правительства Соединенных Штатов, СССР и Соединенного Королевства согласны с Правительством Ирана в том, что любые экономические проблемы, которые встанут перед Ираном после окончания военных действий, должны быть полностью рассмотрены наряду с экономическими проблемами, которые встанут перед другими членами Об'единенных наций,—конференциями или международными организациями, созванными или созданными для обсуждения международных экономических вопросов.

Правительства Соединенных Штатов, СССР и Соединенного Королевства едины с Правительством Ирана в своем желании сохранить полную независимость, суверенитет и территориальную неприкосновенность Ирана. Они рассчитывают на участие Ирана совместно с другими миролюбивыми нациями в установлении международного мира, безопасности и прогресса после войны, в соответствии с принципами Атлантической Хартии, которую подписали все четыре Правительства.

ЧЕРЧИЛЛЬ
СТАЛИН
РУЗВЕЛЬТ

1 декабря 1943 года.

Подтверждение решимости уничтожить Германские вооруженные силы.

Обязательство работать вместе не только в военное, но и в мирное время.

Гарантировалась независимость и территориальная целостность Ирана.

Вступление СССР в войну против Японии

Сталин впервые официально и твердо пообещал Рузвельту и Черчиллю, что СССР вступит в войну на Дальнем Востоке сразу после окончательного разгрома Германии.



Ялтинская конференция

Проводилась для решения вопросов о репарациях Германии, по определению принципов послевоенного устройства мира, раздела сфер влияния и создания ООН.

Проводилась с 4 по 11 февраля 1945г. в крымском городе Ялта.

Основные военные и политические решения

Планы по окончанию войны

Послевоенная Германия

Планы по созданию ООН

Репарации

Польский вопрос

Планы по окончанию войны

Было объявлено о «самой тесной координации военных усилий трех союзников».

План предусматривал, что после капитуляции войска трех держав (с участием Франции) займут отведенные им зоны оккупации.

Стремление к безоговорочной капитуляции Германии.

Послевоенная Германия

Было решено разделить Германию на зоны оккупации:

Советская -> восточная Германия

Британская -> северо-запад

Американская -> юг и центр

Французская -> юго-запад

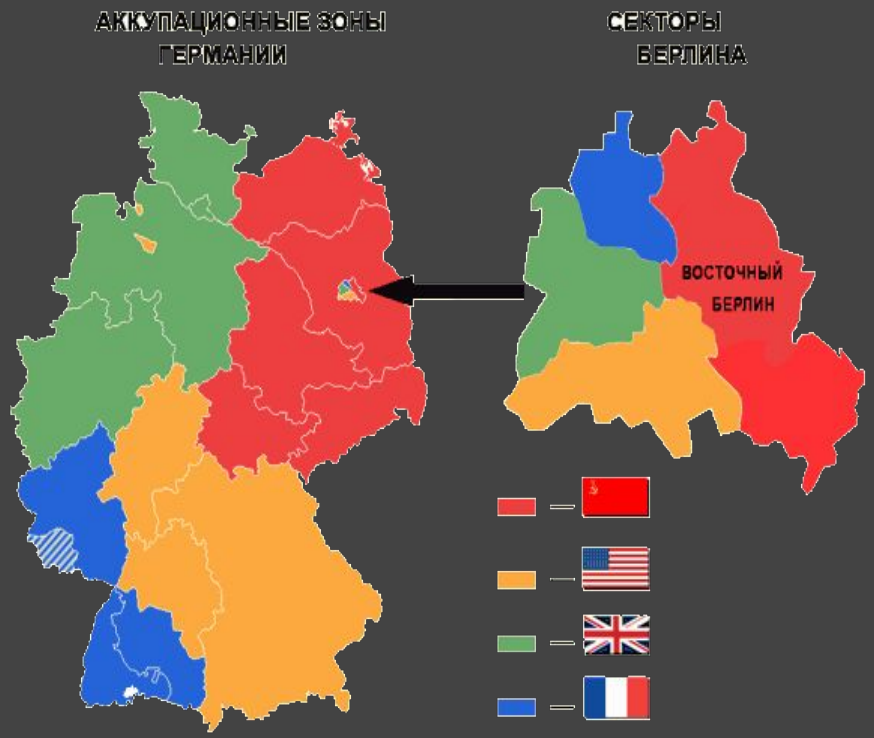

Польский вопрос

Было согласовано, что восточная граница Польши пройдет по линии Керзона.

Компенсацией за утрату восточных земель стало значительное расширение территории Польши на западе и севере за счет Германии.

Было решено реорганизовать просоветское «Временное правительство».

Польша окончательно вошла в сферу влияния СССР.

Репарации

Германия должна возместить убытки, причиненные войной, в максимально возможной мере.

В качестве основы для обсуждения была принята сумма в 20 миллиардов долларов.

50% от этой суммы получит Советский Союз, который понес наибольший ущерб.

Планы по созданию ООН

Рузвельт, Черчилль и Сталин заявили о решимости создать всеобщую международную организацию для поддержания мира и предотвращения новых войн.

Лидеры договорились созвать Конференцию Объединенных Наций в Сан-Франциско для разработки Устава.

Потсдамская конференция

Окончательное решение вопроса о судьбе Германии после её капитуляции и координация действий против Японии.

Проводилась с 17 июля по 2 августа 1945г. в немецком городе Потсдам.

Основные военные и политические решения

Границы Европы

Политика четырёх “Д”

Ультиматум Японии

Создание совета министров иностранных дел

Мирные договоры

Границы Европы

Был подтверждён окончательный раздел Германии на зоны оккупации.

Европа разделилась на сферы влияния: западная - США + Великобритания, восточная - СССР.

Был подтвержден план по разделу Польши.

MAP ABOVE SHOWS NEW BOUNDARIES THAT HAVE BEEN MARKED ON FACE OF EUROPE AS RESULT OF FIVE PEACE TREATIES WITH AXIS SATELLITES SIGNED IN PARIS

TREATIES SETTLE NEW EUROPEAN BOUNDARIES

During World War II, mapmakers were driven frantic keeping track of Europe's boundaries. They shifted as Germany and the U.S.S.R. sparred in the north and east, then snapped apart after the Germans broke loose. Millions of lives were lost before Europe's numerous and complicated borders were put back roughly where they were before.

The general form of these postwar boundaries can be seen from the map above. Based on the treaty terms signed Feb. 10 in Paris between the Allied powers and Hitler's five "satellites," it shows past and present boundaries as well as territory ceded by these and previous agreements (*in dark red*); territory ceded *de facto* to the U.S.S.R. and Poland (*in light red*); and such countries as Lithuania, Latvia and Estonia which no longer exist and have been absorbed by the U.S.S.R. Germany may undergo further territorial changes after the Big Four meeting to be held in Moscow on March 10 to frame the German and Austrian peace treaties, but most of the major territorial disputes are settled, although some, particularly those concerning Italy, will continue to be protested. For detailed maps of individual trouble spots, see next page.

Политика четырёх “Д”

Денацификация - ликвидация нацистских организаций и влияния нацистской идеологии.

Демилитаризация - полное разоружение Германии, роспуск вермахта.

Демократизация - подготовка к восстановлению демократической жизни.

Декартелизация - ликвидация монополий и картелей, поддерживавших нацизм.

Создание совета министров иностранных дел

Создан 1 августа 1945г.

В состав этого органа вошли главы внешнеполитических ведомств СССР, Великобритании, США, Франции и Китая — постоянных членов Совета Безопасности ООН.

Составление мирных договоров для Италии, Румынии, Болгарии,

Венгрии и Финляндии.



Ультиматум Японии

Предъявили США, Великобритания и Китай.

Требования - безоговорочная капитуляция всех японских ВС.

Реакция - политика “мокусацу”

Мирные договоры

Подписаны мирные договоры в Париже с европейскими странами в 15 сентября 1947г.

Между США, Великобританией, СССР и бывшими союзниками Германии.

Были подписаны документы, регламентирующие отношения бывших союзников германии с СССР.

Спасибо за внимание!